Interactive Map of the State of Tamaulipas (1)

- A partir de una API de Mapas y de Polígonos de municipios del INEGI, se implementó una de MAPAS
- El usuario navega sobre el mapa de tamaulipas y selecciona un punto de su interes

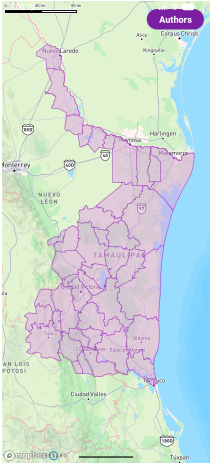

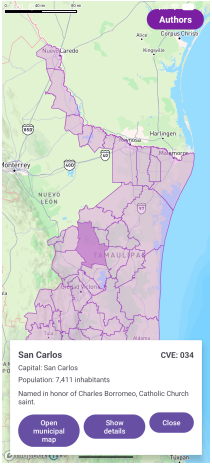

* César Euresti, Walter Leonardo Loera-Gomez, and Emanuel Hernandez-Aguirre. *Interactive Map of the State of Tamaulipas*. Informe técnico proyecto de asignatura "Desarrollo de Aplicaciones Móviles". Universidad Politécnica de Victoria, 2025

Interactive Map of the State of Tamaulipas (2)
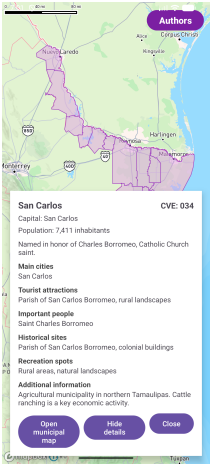
- Se resaltan las atracciones específicas de ese
- Se despliega información del municipio seleccionado